INSTITUCIÓN EDUCATIVA COLEGIO GENERAL SANTANDER

CARTILLA MOVILIDAD SEGURA

EDUCACION BÁSICA PRIMARIA, 4° Y 5°

VILLA DEL ROSARIO
2024

CARTILLA MOVILIDAD SEGURA – 4° A 5° PRIMARIA

Dr. JAIME CÁRDENAS SANTOS - Rector

Mg. Sc. ARTURO ORTIZ ARISMENDY – Coordinador Académico

Esp. YASMIN DE LA MERCED PEÑA CONTRERAS – Coordinadora Convivencia Escolar – Sede Central - JM

Esp. NUBIA ROSA MONSALVE FUENTES – Coordinadora Convivencia Escolar - Sede Central - JT

Mg. GERSON BOTELLO SARMIENTO - Coordinador Convivencia Escolar – Sede Pedro Fortoul

Dr. PABLO ARTURO JAIMES ESPINOSA – Coordinador Convivencia Escolar - Sede Francisco de Paula Santander

Mg. ÁLVARO EDISON MARTÍNEZ DELGADO. Docente Media Técnica.

Mg. JULIO GERMÁN RUBIO ESCALANTE, Docente Líder proyecto Movilidad Segura.

Estudiantes Media Técnica: Contenidos Digitales, JM (11-02)

Jonathan Josué Pérez Blanco

Juana Valentina Rangel Lizcano

Joel Alexander Rodríguez Ramírez

Julián Andrés Rubio Eugenio

Educación y seguridad vial, referentes legales.

La Resolución 64/255, del 1° de marzo de 2010, de la Asamblea General de las Naciones Unidas, propugnando el mejoramiento de la seguridad vial en el mundo, reconoció que la mortalidad por colisiones en accidentes de tránsito tiene una enorme incidencia en todo el mundo y que cada año resultan heridas entre veinte a cincuenta millones de personas a consecuencia de accidentes de tránsito no mortales, muchas de ellas con secuelas de discapacidad permanente.

El Ministerio de Educación Nacional, a través de la Ley 1503 de 2.011, Promueve la formación de hábitos, comportamientos y conductas en la vía. Reconoce que los actores de la vía, son todas las personas que asumen un rol determinado, para hacer uso de las vías, con la finalidad de desplazarse entre un lugar u otro, por tanto, se consideran actores de tránsito y de la vía los peatones, los transeúntes, los pasajeros y conductores de vehículos automotores y no automotores, los motociclistas, los ciclistas, los acompañantes, los pasajeros, entre otros.

El artículo 55 del Código Nacional de Tránsito hace referencia al comportamiento del conductor, pasajero o peatón y enuncia que toda persona que tome parte en tránsito debe comportarse de tal manera que no obstaculice, perjudique o ponga en riesgo a las demás. Por ello, debe conocer y cumplir las normas y señales de tránsito que le sean aplicables, así como obedecer las indicaciones que les den las autoridades de tránsito.

La Constitución Política de Colombia establece la importancia de fomentar prácticas democráticas para el aprendizaje de los principios y valores de la participación ciudadana en las instituciones educativas del país (art. 41), con el fin de propiciar en las colombianas y colombianos el respeto a los derechos humanos, a la paz y a la democracia (art. 67).

En el mismo sentido, la Ley General de Educación (Ley 115 de febrero 8 de 1994) dispone que la educación sea un proceso de formación permanente, personal, cultural y social que se fundamenta en una concepción integral de la persona humana, de su dignidad, derechos y deberes (art. 1).

La Secretaría de Educación Departamental, adoptó la Ordenanza No. 0019 del 12 de diciembre de 2.019 de la Asamblea del Departamento Norte de Santander y, en articulación con la Secretaría de Tránsito Departamental, como lineamiento de política pública de seguridad vial en el Departamento Norte de Santander de acuerdo con su vigencia y sus partes estructurales, en cuanto a diagnóstico, parte estratégica e iniciativas para los pilares fortalecimiento de la gestión institucional, comportamiento humano, vehículos seguros, infraestructura vial y atención a víctimas de siniestros viales.

La movilidad, para que sea segura, requiere que en los actores de la vía se desarrollen cinco competencias: reconocer y navegar efectivamente por el entorno, moverse de forma idónea dependiendo del modo de transporte utilizado, valorar en la movilidad el riesgo y la vulnerabilidad ante el mismo, asumir la regulación existente y ser corresponsable en la movilidad segura y cooperadora de los demás. Competencias relacionadas con un modelo preventivo, ligado también con la formación, todo lo cual permite garantizar su correcta articulación al proceso de enseñanza y aprendizaje.



PRESENTACIÓN

El Ministerio de Salud y Protección Social, definió dentro de sus prioridades la inseguridad vial como un problema de salud pública, obedeciendo a las altas cifras de fallecidos, lesionados y discapacitados que dejan los incidentes viales cada año. Un dato solo del año 2.017, según las cifras del Observatorio Nacional de Seguridad Vial, fallecieron 6.718 personas y resultaron lesionadas 40.088.
De acuerdo con cifras de la Agencia Nacional de Seguridad Vial (ANSV), en el año 2.021, fallecieron 7.104 personas en accidentes de tránsito.

La presente cartilla está dirigida a los docentes y estudiantes del Nivel Preescolar, Grado Transición, del Colegio General Santander, para ser desarrollada en las Sedes Educativas Francisco de Paula Santander y Pedro Fortoul, como una propuesta del Proyecto Movilidad Segura, para una mejor movilidad, más saludable y sostenible.
Este es el espacio más propicio para ir formando al nuevo ciudadano en un enfoque de educación vial, con valores éticos, respetuosos de los derechos humanos, cumplidores de sus deberes sociales y con un espíritu para convivir en paz.

La estructura se definió con base en el documento No. 27 del Ministerio de Educación Nacional. Acorde a la malla curricular, se proponen cinco competencias para ser desarrolladas en un conjunto de grados como son: Transición, Primero a Tercero, Cuarto y Quinto, Sexto y Séptimo, Octavo y Noveno, Décimo y Undécimo.

Las competencias a desarrollar son:
Asumir la regulación: Acatamiento a la gestión (planificación, legislación, regulación, control) de la autoridad para mantener vigentes las normas objetivas y subjetivas de la movilidad, asumidas como un acuerdo social que procura el mayor bien para el mayor número.

Corresponsabilidad vial: Estado de desarrollo moral en el cual el individuo puede asumir el deber de garantizar al otro su derecho a movilizarse con libertad de forma segura y oportuna.

Valoración en la movilidad del riesgo y la vulnerabilidad: Decisión autónoma de afrontar un riesgo en la movilidad, luego de sopesar la capacidad de tolerarlo y valorar las consecuencias de su decisión.

Comprensión del entorno: Aprender las condiciones de uso y aprovechamiento Del espacio público, así como de los factores condicionantes del tránsito, para garantizar la capacidad de guiar el comportamiento a través de señales propias y externas.

Movilidad idónea según modo: Asumir que el derecho a desplazarse libremente es intervenido por el modo de transporte utilizado al realizar esta acción, así como por la presencia de otros en la vía.

La cartilla cuenta con veinte fichas de trabajo para ser desarrolladas por los estudiantes a lo largo del año lectivo.

Entre los materiales a utilizar para el desarrollo de la actividad propuesta, se determinan: colores, colbón, plastilina, papel rasgado, témpera, entre otros.

En la guía para el docente, entre las recomendaciones se establece la información que se debe precisar para ser transmitida al estudiante y que le permita construir su concepto en una forma más acertada y en línea con el objetivo del proyecto.

Contenido

Guía del Docente **10**

Ficha 1: El peatón – Competencia: Asumir la regulación 10

Ficha 2: El semáforo – Competencia: Asumir la regulación 11

Ficha 3: Señales Reglamentarias – Competencia: Asumir la regulación 12

Ficha 4: Señales Preventivas – Competencia: Asumir la regulación 13

Ficha 5: Señales Informativas – Competencia: Asumir la regulación 14

Ficha 6: Ceda el paso – Competencia: Asumir la regulación. 15

Ficha 7: Señal de pare – Competencia: Asumir la regulación. 16

Ficha 8: La cebra – Competencia: Asumir la regulación. 17

Ficha 9: Invasión de carril – Competencia: Corresponsabilidad vial 18

Ficha 10: Límites de velocidad – Competencia: Corresponsabilidad vial 19

Ficha 11: Cruzar por sitios prohibidos – Competencia: Corresponsabilidad vial. 20

Ficha 12: Conductor de bicicleta – Competencia: Corresponsabilidad vial. 21

Ficha 13: El respeto: la llave que abre el transporte público – Competencia: Corresponsabilidad vial. 22

Ficha 14: Distracción en la vía como peatón – Competencia: Valoración en la movilidad del riesgo y la vulnerabilidad 23

Ficha 15: Comportamientos inseguros de los peatones en la vía pública – Competencia: Valoración en la movilidad del riesgo y la vulnerabilidad. 24

Ficha 16: Cruzar la vía: Observando cada uno de los lados – Competencia: Valoración en la movilidad del riesgo y la vulnerabilidad. 25

Ficha 17: Puntos cardinales– Competencia: Comprensión del entorno 26

Ficha 18: Zonas peatonales– Competencia: Movilidad idónea 27

Ficha 19: Visión periférica– Competencia: Movilidad idónea 29

Ficha 20: Cinturón de seguridad– Competencia: Movilidad idónea 30

Fichas **31**

El semáforo 33

Señales Reglamentarias 34

Señales Preventivas 35

Señales Informativas 36

Ceda el paso 37

Señal de pare 38

La cebra 39

Invasión de carril....40
Límites de velocidad....41
Cruzar por sitios prohibidos....42
Conductor de bicicleta....43
El respeto....44
Distracción en la vía como peatón....45
Comportamientos inseguros de los peatones en la vía pública....46
Cruzar la vía....47
Puntos cardinales....48
Zonas peatonales....49
Visión periférica....50
Cinturón de seguridad....51
Referencias....**52**

Guía del Docente 4° y 5°

Guía del Docente

Ficha 1: El peatón – Competencia: Asumir la regulación

El peatón, como actor vial, debe comportarse en forma responsable y no debe obstaculizar, perjudicar o poner en riesgo a las demás personas, y debe conocer y cumplir las normas y señales de tránsito.

Indicaciones

- Un peatón respetuoso de las normas viales, acata las señales luminosas de los semáforos.
- El tránsito de peatones por las vías públicas, se hará por fuera de las zonas destinadas al tránsito de vehículos.
- Mirar hacia la derecha y hacia la izquierda antes de cruzar la calzada.
- Cuando un peatón requiera cruzar una vía vehicular, lo hará respetando las señales de tránsito y cerciorándose de que no existe peligro para hacerlo.
- Deben evitar invadir la zona destinada al tránsito de vehículos.
- Detenerse cuando está cerca de un garaje, asegurándose que no va a salir o entrar un vehículo, antes de continuar la marcha.
- Utilizar el puente peatonal cuando estén en el área, para cruzar con seguridad la autopista.

- Deben evitar colocarse delante o detrás de un vehículo que tenga el motor encendido.
- Deben evitar cruzar la vía atravesando el tráfico vehicular en lugares en donde existen pasos peatonales.
- Deben evitar subirse o bajarse de los vehículos, estando éstos en movimiento, cualquiera que sea la operación o maniobra que estén realizando.
- Dentro del perímetro urbano, el cruce debe hacerse sólo por las zonas autorizadas, como los puentes peatonales, los pasos peatonales y las bocacalles.
- No hacer uso del celular cuando esté atravesando la calzada.

Ficha 2: El semáforo – Competencia: Asumir la regulación

SEMÁFORO ANÁLOGO

ROJO: El vehículo detiene la marcha. Cruzan los peatones.

AMARILLO: Precaución.

VERDE: Avanzan los vehículos. Los peatones se detienen en la acera.

SEMÁFORO PEATONAL

PEATÓN - ROJO:

No avanza. Detiene la marcha.

PEATÓN - VERDE:

Avanza, cruzando la calle por la cebra.

Un semáforo es un dispositivo eléctrico de señalización vial, que sirve para regular la circulación de vehículos y peatones en las vías públicas, asignando el derecho de paso a los vehículos y peatones según el uso de colores rojo, amarillo y verde y sus diferentes significados.

Indicaciones para el peatón

- Respetar siempre el semáforo, esperando la luz roja y nunca cruzar en una curva o en zonas donde no se pueda ver si viene un vehículo cerca, es importante fijarse a que distancia y velocidad vienen los vehículos.

- Evitar distraerse por el uso de dispositivos electrónicos, como celular o audífonos. La privación de los sentidos, o aislamiento del medio ambiente, impide escuchar sonidos del entorno local y aumenta las probabilidades de sufrir un accidente.

Indicaciones para el ciclista

El ciclista debe ser consciente que la bicicleta es un vehículo con derecho de circular por la calzada, y su obligación, es la de frenar ante el semáforo cuando la luz está en rojo.

Avanza, cuando la luz haya cambiado a verde.

Ficha 3: Señales Reglamentarias – Competencia: Asumir la regulación



https://www.motor.com.co/

Tiene por objeto indicar al usuario de la vía las limitaciones, prohibiciones o restricciones sobre su uso, y cuya violación constituye falta. En las señales circulares los colores distintivos son: anillos y líneas oblicuas en rojo, fondo blanco y símbolos negros. Se identifica con el código SR.

Indicaciones

- Esta categoría tiene la responsabilidad de señalar las prohibiciones, límites y restricciones de las áreas donde están colocadas.
- Estas normativas son obligatorias para todos los conductores y el incumplimiento puede resultar en sanciones de tránsito.
- En Colombia, el no acatar estas señales podría conllevar multas de hasta 15 salarios mínimos diarios legales vigentes.
- Las señales reglamentarias se distinguen con facilidad debido a su forma circular, color rojo y símbolos en negro.

Ficha 4: Señales Preventivas – Competencia: Asumir la regulación

El propósito de estas señales es brindar información anticipada y precaución al conductor acerca de las condiciones de la carretera y los riesgos potenciales durante su trayecto. Tienen un fondo amarillo, con símbolos negros y forma de rombo.

Indicaciones

- El principal objetivo de las señales preventivas es prevenir accidentes al alertar a los conductores sobre condiciones peligrosas.
- Identificadas con el código SP, estas señales desempeñan un papel crucial en la seguridad vial, advirtiendo sobre posibles riesgos y garantizando una conducción más segura.
- Estas señales se identifican con el código SP y adoptan la forma de un cuadrado con diagonal vertical rombo, con excepciones para señales específicas como el

paso a nivel, que utiliza la conocida cruz de San Andrés, y la flecha direccional, que se presenta en forma rectangular.

- En vías urbanas o de jerarquía inferior, se ubican a una distancia variable entre 60 y 80 metros antes del riesgo.
- El uso de colores en estas señales sigue las especificaciones de la Norma Técnica Colombiana NTC 473. Por lo general, el amarillo se utiliza para el fondo, mientras que el negro se emplea para orlas, símbolos, letras y números.

Ficha 5: Señales Informativas – Competencia: Asumir la regulación

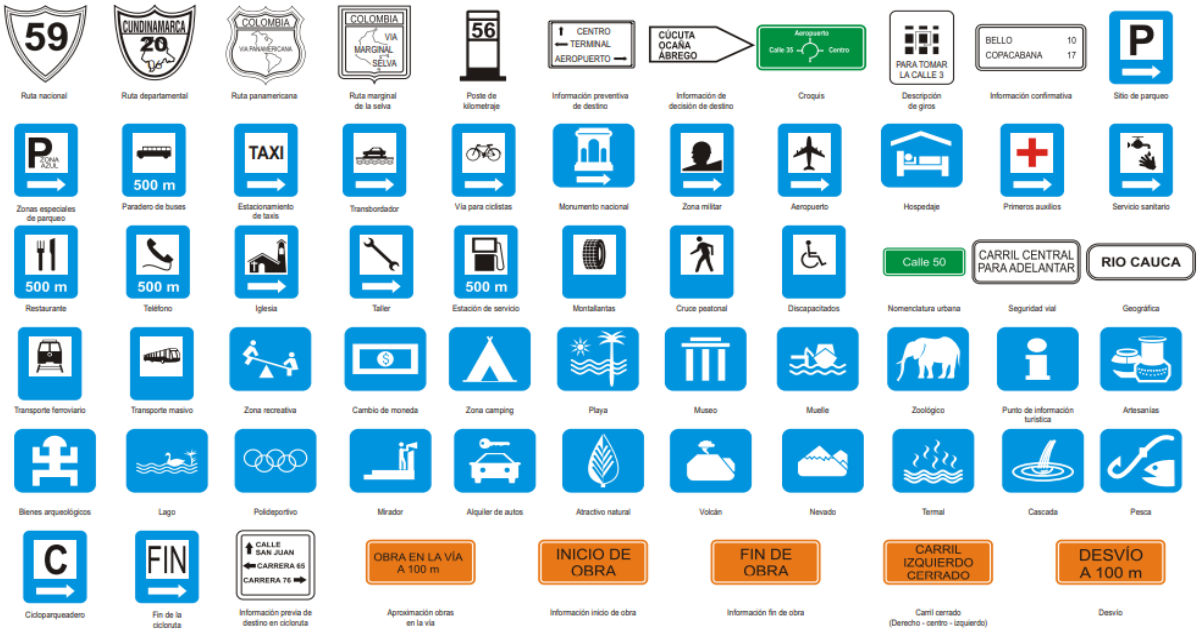

Tiene por objeto guiar al usuario de la vía, suministrándole información de localidades, destinos, direcciones, sitios especiales, distancias y prestación de servicios. Por lo general son rectangulares, con algunas excepciones. Los colores distintivos son: fondo azul, textos y flechas blancas y símbolos negros. Se identifican con el código SI.

Indicaciones

En particular, se utilizan para informar sobre: a. Direcciones hacia destinos, calles o rutas

b. Hacia dónde conduce la vía

c. Enlaces o empalmes con otras vías

d. Carriles apropiados para cada destino

e. Inicio de la salida a otras vías

f. Distancias a que se encuentran los destinos

g. Hito kilométrico a lo largo de la vía

h. Identificación de rutas y calles

i. Servicios generales

j. Lugares de atractivo turístico existentes en las inmediaciones de la vía

k. Nombres de ciudades, ríos, puentes, calles, parques, lugares históricos y otros

l. Cualquier otra información de importancia para los conductores.

Ficha 6: Ceda el paso – Competencia: Asumir la regulación.

Señala la obligatoriedad de ceder el paso a todos los vehículos que circulen por la vía próxima o por aquella a la que se pretende acceder, cualquiera que sea el lado por el que se aproximen, llegando a detener el paso cuando la situación lo requiera.

Indicaciones

- Respetar la señal de ceder el paso es esencial para mantener la seguridad en las carreteras y promover una convivencia armoniosa entre los conductores. Al detenerse correctamente en una intersección y ceder el paso a los vehículos que tienen el derecho de paso, se evitan potenciales colisiones y se reduce significativamente el riesgo de accidentes.

- El ciclista como actor vial, debe ceder el paso para que los peatones puedan cruzar sin sentirse en peligro.
- Los ciclistas tienen prioridad de paso respecto a los vehículos de motor cuando circulan por un carril con paso para ciclistas.
- El conductor de un vehículo automotor, tiene la obligación de ceder el paso en la intersección a los vehículos que circulen por la vía a la que se aproxima o al carril al que pretende incorporarse.
- En caso de que exista un semáforo, se da prioridad a la señal luminosa si es verde, y se extrema la precaución si es amarilla.

Ficha 7: Señal de pare – Competencia: Asumir la regulación.

Es utilizada para que el actor vía que la encuentra, detenga completamente su vehículo y pueda reanudar su marcha únicamente cuando no vea las condiciones para evitar totalmente un accidente de tránsito.

Además, están ubicadas en sitios que le aseguran al conductor una buena visibilidad.

Indicaciones

- En primer lugar, debemos tener en cuenta que la señal de pare indica la obligatoriedad de parar, si no existe ninguna señal pintada en la carretera o si nos encontramos justo antes de un cruce.
- Desde el momento en el que se observa la señal, se debe frenar el vehículo poco a poco, para que cuando se llegue a la misma, se pueda detener totalmente la marcha y no tener que hacerlo de forma violenta.

- La señal de Pare indica detención obligatoria, y esta detención, debe ser completa del vehículo.
- La realidad demuestra que, para la mayoría de los conductores, es una detención que se aplica a conveniencia. Esto es producto de falta de cultura ciudadana y la carencia de educación vial que aqueja a la sociedad.

Ficha 8: La cebra – Competencia: Asumir la regulación.

Las cebras son una señal utilizada en muchos lugares del mundo para indicar pasos seguros para los peatones.

Indicaciones

- Tiene derecho el peatón a cruzar cuando el semáforo peatonal está en verde o cuando no haya semáforo.
- El peatón debe asegurarse de que no haya vehículos cercanos antes de cruzar.
- El peatón no debe cruzar la calle distraído por dispositivos electrónicos.
- Se ubican en los semáforos, pero en algunas zonas el flujo peatonal, ha obligado a demarcar otras áreas que no necesariamente coinciden con un cruce semaforizado.
- La cebra peatonal es un elemento vital en la planificación urbana, un espacio marcado en las vías públicas con rayas blancas alternas que indican un área segura para que los peatones crucen las calles, teniendo así la prelación ante los vehículos.

- Su diseño distintivo y su presencia estratégica en intersecciones y zonas de tránsito denotan una prioridad de paso para quienes caminan, creando un entorno más seguro en el flujo vehicular.
- Este recurso esencial no solo es un símbolo de seguridad vial, sino que también funciona como un punto de encuentro entre la movilidad peatonal y vehicular, regulando y facilitando el tránsito de manera ordenada.
- Además de su función física, la cebra peatonal también representa un compromiso social en la promoción de la convivencia entre conductores y peatones, fomentando una convivencia armoniosa en nuestras calles.
- Su origen se remonta a la planificación urbana de la antigua ciudad romana de Pompeya, donde se implementó este tipo de diseño para organizar el flujo del tráfico y facilitar el acceso a distintas zonas de la urbe.

Ficha 9: Invasión de carril – Competencia: Corresponsabilidad vial

La invasión a diferencia del cambio se produce cuando de manera intempestiva, abrupta, irregular, sin medidas ni precauciones se ingresa al carril de al lado; derecho, izquierdo y en ocasiones hasta contrario sin tomar las debidas precauciones.

Indicaciones

- La invasión al carril es una de las causas principales de los accidentes de tránsito.
- Por lo general, el vehículo que se introduce de manera parcial o por completo al carril contrario a su marcha, es el culpable de todo incidente que ocurra por esa acción.

- Para evitar situaciones de riesgo, se debe conducir con mucha prudencia y paciencia, si el vehículo que marcha adelante, no fluye o avanza, o se considera que obstaculiza la vía.
- Para adelantar un vehículo se debe tener total visión de la vía y no se debe exceder la velocidad.

Ficha 10: Límites de velocidad – Competencia: Corresponsabilidad vial

En vías urbanas, las velocidades máximas serán de sesenta (60) kilómetros por hora, excepto cuando las autoridades competentes por medio de señales indiquen velocidades distintas.

Indicaciones

- La separación entre dos (2) vehículos que circulen uno tras de otro en el mismo carril de una calzada, será de acuerdo con la velocidad.
- Para velocidades de hasta treinta (30) kilómetros por hora, diez (10) metros.
- Para velocidades entre treinta (30) y sesenta (60) kilómetros por hora, veinte (20) metros.
- Para velocidades entre sesenta (60) y ochenta (80) kilómetros por hora, veinticinco (25) metros
- Para velocidades de ochenta (80) kilómetros en adelante, treinta (30) metros o la que la autoridad competente indique.

- En todos los casos, el conductor deberá atender al estado del suelo, humedad, visibilidad, peso del vehículo y otras condiciones que puedan alterar la capacidad de frenado de éste, manteniendo una distancia prudente con el vehículo que antecede.
- En la autopista internacional Simón Bolívar, que comunica a Cúcuta con Villa del Rosario, la velocidad mínima es de 30 km/h y una máxima de 60 km/h.

Ficha 11: Cruzar por sitios prohibidos – Competencia: Corresponsabilidad vial.

Los actores viales deben cumplir con las normas viales, enriqueciendo la cultura vial, evitando poner en riesgo la vida de quienes circulan en cualquier sentido.

Indicaciones

- Evitar invadir la zona destinada al tránsito de vehículos, o transitar en ésta en patines, monopatines, patinetas o similares.
- Llevar, sin las debidas precauciones, elementos que puedan obstaculizar o afectar el tránsito.
- Cruzar por sitios no permitidos o cruzar por encima del separador de la vía.
- Colocarse delante o detrás de un vehículo que tenga el motor encendido.
- Cruzar la vía atravesando el tráfico vehicular en lugares en donde existen pasos peatonales.

- Los peatones deben evitar transitar por túneles y puentes.
- Los conductores de vehículos deben evitar transitar por los andenes o aceras, ya que estos pasos, son únicamente para uso de los peatones.

Ficha 12: Conductor de bicicleta – Competencia: Corresponsabilidad vial.

Al igual que todo conductor, los ciclistas deben cumplir cabalmente las normas exigidas en el Código Nacional de Tránsito, en especial, las normas generales para **bicicletas y triciclos.**

Indicaciones

- Las bicicletas y vehículos de impulsión humana, transitarán de acuerdo con las reglas que en cada caso dicte la autoridad de tránsito competente.
- Deben transitar por la derecha de las vías a distancia no mayor de un (1) metro de la acera u orilla y nunca utilizar las vías exclusivas para servicio público colectivo.
- Está prohibido transitar por los andenes o aceras, o puentes de uso exclusivo para los peatones.
- No deben sujetarse de otro vehículo o viajar cerca de otro carruaje de mayor tamaño que lo oculte de la vista de los conductores que transiten en sentido contrario.

- Evitar transportar personas o cosas que disminuyan su visibilidad e incomoden la conducción.
- Deben respetar las señales, normas de tránsito y límites de velocidad.
- Los conductores de bicicleta que transiten en grupo lo harán uno detrás de otro.
- Deben conducir en las vías públicas permitidas o, donde existan, en aquellas especialmente diseñadas para ello.
- Los conductores y los acompañantes cuando hubiere, deberán utilizar casco y elementos de seguridad.
- Los conductores de bicicleta deberán respetar los derechos e integridad de los peatones.

Ficha 13: El respeto: la llave que abre el transporte público – Competencia: Corresponsabilidad vial.

Aprender, entender y comprender la lógica del comportamiento adecuado y cómo se utiliza el transporte público.

Indicaciones

- Evitar escribir o rayar las sillas de los vehículos en donde se transporta.
- Evitar arrojar envolturas de alimentos, recipientes desocupados y/o basura dentro o fuera del vehículo.
- Evitar dejar maletas o elementos grandes que obstaculicen el paso de otros pasajeros.

- Evitar hablar o reír en tono alto mientras estamos acompañados en el transporte público.
- Evitar sentarse en las sillas para mamás embarazadas o con alguna discapacidad física.
- Acciones que impidan relacionarse de manera adecuada con otros pasajeros.

Ficha 14: Distracción en la vía como peatón – Competencia: Valoración en la movilidad del riesgo y la vulnerabilidad.



La distracción al conducir o caminar, es cualquier actividad que desvíe la atención—incluyendo hablar o textear en el teléfono, comer y beber, hablar con la gente mientras se está movilizando.

Indicaciones

- **Usar las aceras**. Cuando están disponibles, son el lugar más seguro para caminar.
- **Mantenerse visible.** Llevar ropa de colores claros con materiales reflectantes podría ayudarte a llamar la atención de los conductores.
- **Mantenerse alerta**. Hay muchos conductores distraídos en la vía pública, así que mantén tu atención en todo momento.
- **Evitar el alcohol y las drogas**. Pueden perjudicar enormemente la capacidad para caminar con seguridad y tomar buenas decisiones.

- **Cruzar las calles en las esquinas**. Si bien puede ser tentador cruzar a mitad de cuadra, aquí es donde ocurren muchas lesiones.
- **Mirar hacia ambos lados**. Mira a la izquierda, luego a la derecha y luego a la izquierda nuevamente antes de cruzar.
- **Tener especial cuidado en las intersecciones**. Es ahí donde muchos conductores podrían no ceder el derecho de paso mientras doblan hacia otra calle.
- **Siempre evita textear y usar el teléfono mientras caminas**. Al caminar o cruzar una calle, evita el uso de teléfono celular y de audífonos para que puedas prestar atención a tu entorno. Textear mientras caminas te distrae y te dificulta la vigilancia del tráfico y de los obstáculos en tu camino.
- **Cuidado con los vehículos estacionados**. Los estacionamientos pueden ser especialmente peligrosos ya que muchos conductores tienen una visión limitada al retroceder. Los conductores podrían no esperar personas caminando por ahí y se necesita prestar atención adicional.
- **Hay que ser predecibles**. Tu próximo movimiento debería ser obvio para el conductor. La comunicación no verbal efectiva, tal como un simple saludo con la mano, puede ayudar a marcar la diferencia en la interacción entre un conductor y un peatón.

Ficha 15: Comportamientos inseguros de los peatones en la vía pública – Competencia: Valoración en la movilidad del riesgo y la vulnerabilidad.



Indicaciones

- Jugar en la vía ignorando que la calzada es para la movilidad de los vehículos.
- Evitar cruzar la calzada sin observar los peligros que puede enfrentar.
- Evitar salir por delante de un vehículo que se encuentra detenido en la vía.
- Evitar transitar por la calzada haciendo caso omiso del flujo vehicular.
- Evitar pararse sobre la calzada obligando al conductor del vehículo a realizar maniobras peligrosas.
- Evitar cruzar la calzada en diagonal, ya que el tramo que va a recorrer es más largo y se hace más vulnerable aun accidente.
- Evitar pasar el semáforo cuando está en verde.
- Evitar descender o subir al vehículo estando en marcha.

Ficha 16: Cruzar la vía: Observando cada uno de los lados – Competencia: Valoración en la movilidad del riesgo y la vulnerabilidad.

OBSERVACIÓN DE LA VÍA, ANTES DE CRUZAR.

La calzada no se debe cruzar por cualquier lado, sino, haciendo uso de la cebra. Antes de avanzar, por seguridad, se debe mirar en ambos sentidos de la vía.

Indicaciones

- Los niños tienen una visión periférica más limitada que los adultos, lo que significa que pueden no ver los vehículos que se acercan desde los lados.

- Es importante enseñarles a los niños a mirar en ambas direcciones antes de cruzar la calle, incluso si el semáforo está en rojo para los vehículos.
- Si existe semáforo en el paso de cebra, se debe tener en cuenta que el peatón avanza, cuando la luz esté en rojo.
- El cruce de la calzada, no se debe realizar por otro punto diferente de la cebra, porque el grado de vulnerabilidad aumenta.
- Es crucial enseñarles a los niños a esperar en la acera hasta que el semáforo esté en rojo para los vehículos o verde para los peatones.

Ficha 17: Puntos cardinales– Competencia: Comprensión del entorno

Ubicación espacial acorde a los puntos cardinales: Norte, Sur, Este y Oeste. Para poder orientarnos, tenemos que conocer uno de los puntos cardinales y el Sol nos ayudará a ello porque siempre sale por el Este (Oriente) y se oculta por el Oeste (Occidente).

Indicaciones

- El **Este** corresponde al espacio de la parte derecha de un punto geográfico determinado. Una persona puede orientarse en función del movimiento del Sol en el horizonte, si señala con el brazo derecho hacia donde sale el Sol este lugar corresponde con el Este.

- El **Oeste** corresponde al espacio de la parte izquierda de un punto geográfico determinado. Cuando nos orientamos en cualquier lugar de la Tierra, como en el caso anterior, coincide con el brazo izquierdo, el que señala el lugar donde se pone el Sol.
- El **Norte** corresponde al espacio de la parte superior de un punto geográfico determinado. Delante cuando nos orientamos en cualquier lugar de la Tierra.
- El **Sur** corresponde al espacio de la parte inferior de un punto geográfico determinado. Detrás cuando nos orientamos en cualquier lugar de la Tierra.
- Además, el espacio que existe entre dos puntos cardinales puede designarse mediante los denominados puntos cardinales compuestos: Noreste, Noroeste, Sureste y Suroeste.
- En Villa del Rosario, las carreras (avenidas en Cúcuta), van del punto cardinal norte a sur o viceversa. Las calles van del punto cardinal oriente al occidente o viceversa.
- El conductor de un vehículo que transite por la carrera o avenida, tiene la prelación o preferencia de avanzar. El conductor que viene por la calle debe hacer el pare.

Ficha 18: Zonas peatonales– Competencia: Movilidad idónea



Zonas destinadas para el tránsito exclusivo de peatones. Todos somos peatones, esta es la forma natural de moverse del ser humano. La mayor parte de nuestros días cumplimos muchas de nuestras actividades caminando. Incluso para

llegar a nuestra bicicleta, al transporte público, o a nuestro vehículo particular, lo hacemos como peatones. Por esto tenemos la responsabilidad de cuidarnos y cuidar a los otros.

Indicaciones

- El peatón es el actor vial más vulnerable y continúa representando el mayor número de fatalidades en las vías.
- El modo de desplazamiento peatonal es el más incluyente, vulnerable, económico, cotidiano, ambientalmente amigable y es el que nos permite disfrutar más de la ciudad.
- Ser peatón es mejor para desplazarnos en la ciudad, debido a que nos permite interactuar más con sus espacios, usos y personas.
- Ambientalmente no genera emisiones, contribuye a la movilidad eficiente/sostenible y es de bajo costo en comparación con otros modos de transporte.
- Se puede reducir el número de siniestros que ocurren en la ciudad siguiendo las normas de tránsito y respetando a los peatones, en particular a los niños, personas mayores y peatones en condición de movilidad reducida que transitan por las calles.
- Caminar es una actividad que mejora nuestra calidad de vida.
- Cuando un semáforo **peatonal** está en rojo, el peatón debe abstenerse de cruzar.
- La cebra, es la zona de la calzada, señalizada con dispositivos y pintura, destinada para el cruce de peatones.
- En una autopista, el peatón debe cruzar siempre en forma segura, utilizando le puente peatonal.

Ficha 19: Visión periférica– Competencia: Movilidad idónea

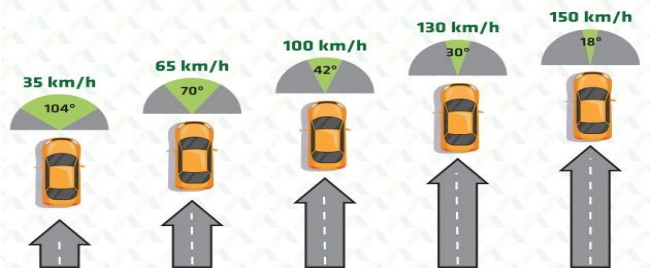

La visión periférica, o visión indirecta, es la visión que se produce fuera del punto de fijación, es decir, lejos del centro de la mirada o, cuando se ve en ángulos amplios, en el "rabillo del ojo". La gran mayoría del área del campo visual está incluida en la noción de visión periférica.

Indicaciones

- Las distracciones y fatigas visuales provocadas por una visión deficiente de los conductores pueden tener mucha influencia en la mayoría de los accidentes.
- Poseer una buena calidad de visión es de vital importancia en la tarea de conducir un vehículo.
- Hay limitaciones naturales relacionadas con la visibilidad durante la noche, la visión periférica, la estimación de la velocidad y las distancias, el procesamiento de la información por el cerebro y otros factores fisiológicos asociados que influyen en el riesgo de participar en un accidente.
- En este sentido se debe destacar que un 80% de la información que recibimos llega a través de nuestros ojos y el 90% de las decisiones que tomamos frente al vehículo que se conduce, depende directamente del estado de nuestra visión.
- Conducir debe requerir el 100% de tu atención. Las causas más comunes de accidentes son por manejar usando el celular, estar comiendo, o ajustar dispositivos sin mirar hacia adelante.

Ficha 20: Cinturón de seguridad– Competencia: Movilidad idónea

Conjunto de tiras, provisto de hebilla de cierre, dispositivos de ajuste y de unión, cuyo fin es sujetar a los ocupantes al asiento del vehículo, para prevenir que se golpeen cuando suceda una aceleración, desaceleración súbita o volcamiento.

Indicaciones

- El cinturón de seguridad se lo deben colocar el conductor y pasajeros antes de que el vehículo inicie la marcha.
- Usar el cinturón de seguridad siempre debe ser una obligación, y no, una opción.
- El cinturón de seguridad sujeta, absorbe energía y protege de lesiones mayores.
- Debe quedar bien ajustado al cuerpo y nunca torcido ni pasar por debajo del brazo, ya que esto podría provocar lesiones considerables o simplemente no proteger.
- Pasa la cinta diagonal sobre la clavícula, entre el cuello y el hombro.
- La banda abdominal sobre las caderas, nunca sobre el abdomen.
- Si el cinturón queda en el cuello o sobre las partes blandas del abdomen, puede causar lesiones graves en un siniestro.
- El cinturón está diseñado para estirarse. Si el asiento está muy adelante, la persona podría golpearse con el manubrio, con partes interiores del vehículo, o dañarse cuando se active el Airbag si el vehículo cuenta con éste.
- En el asiento delantero de los vehículos sólo podrán viajar, además del conductor, una persona mayor de diez (10) años.

Fichas de trabajo Estudiantes 4° y 5°

	INSTITUCIÓN EDUCATIVA **COLEGIO GENERAL SANTANDER** **MUNICIPIO DE VILLA DEL ROSARIO** **PROYECTO MOVILIDAD SEGURA** **EDUCACIÓN BÁSICA PRIMARIA, GRADOS 4 Y 5.**					**CÓDIGO** **GAC01** **Fecha de Aprobación:** **31/01/19**	
SEDE ESCOLAR		**GRADO-JORNADA**		**TEMA**	**El peatón**-Competencia: Asumir la regulación		
ACTIVIDAD	Coloreo el peatón (actor vial). Socializo la respuesta.					**FICHA**	01
NOMBRE			**FECHA**				



EXPLICO:

Escribo cinco actuaciones que debo realizar como peatón

1). _____

2). _____

3). _____

4). _____

5). _____

	INSTITUCIÓN EDUCATIVA **COLEGIO GENERAL SANTANDER** **MUNICIPIO DE VILLA DEL ROSARIO** **PROYECTO MOVILIDAD SEGURA** **EDUCACIÓN BÁSICA PRIMARIA, GRADOS 4 Y 5.**					**CÓDIGO** **GAC01** **Fecha de Aprobación:** **31/01/19**
SEDE ESCOLAR		**GRADO-JORNADA**		**TEMA**	**El semáforo** – Competencia: Asumir la regulación	
ACTIVIDAD	Coloreo el semáforo y explico la función de los colores de las luces. Socializo.				**FICHA**	02
NOMBRE			**FECHA**			

Semáforo análogo vehículos

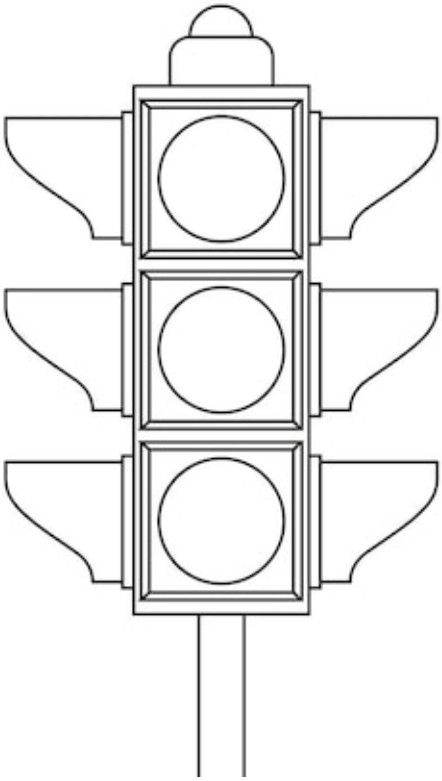

Semáforo digital para los peatones



EXPLICO:

1. ¿Qué indica la luz roja para los peatones? _____

_____

2. ¿Qué indica la luz de color amarillo para los peatones? _____

_____

3. ¿Qué indica la luz de color verde para los peatones? _____

_____

	INSTITUCIÓN EDUCATIVA **COLEGIO GENERAL SANTANDER** **MUNICIPIO DE VILLA DEL ROSARIO** **PROYECTO MOVILIDAD SEGURA** **EDUCACIÓN BÁSICA PRIMARIA, GRADOS 4 Y 5.**					**CÓDIGO** **GAC01** **Fecha de Aprobación:** **31/01/19**
SEDE ESCOLAR		**GRADO-JORNADA**		**TEMA**	**Señales Reglamentarias** – Competencia: Asumir la regulación	
ACTIVIDAD	Coloreo las señales reglamentarias y las explico. Socializo la respuesta.				**FICHA**	03
NOMBRE			**FECHA**			

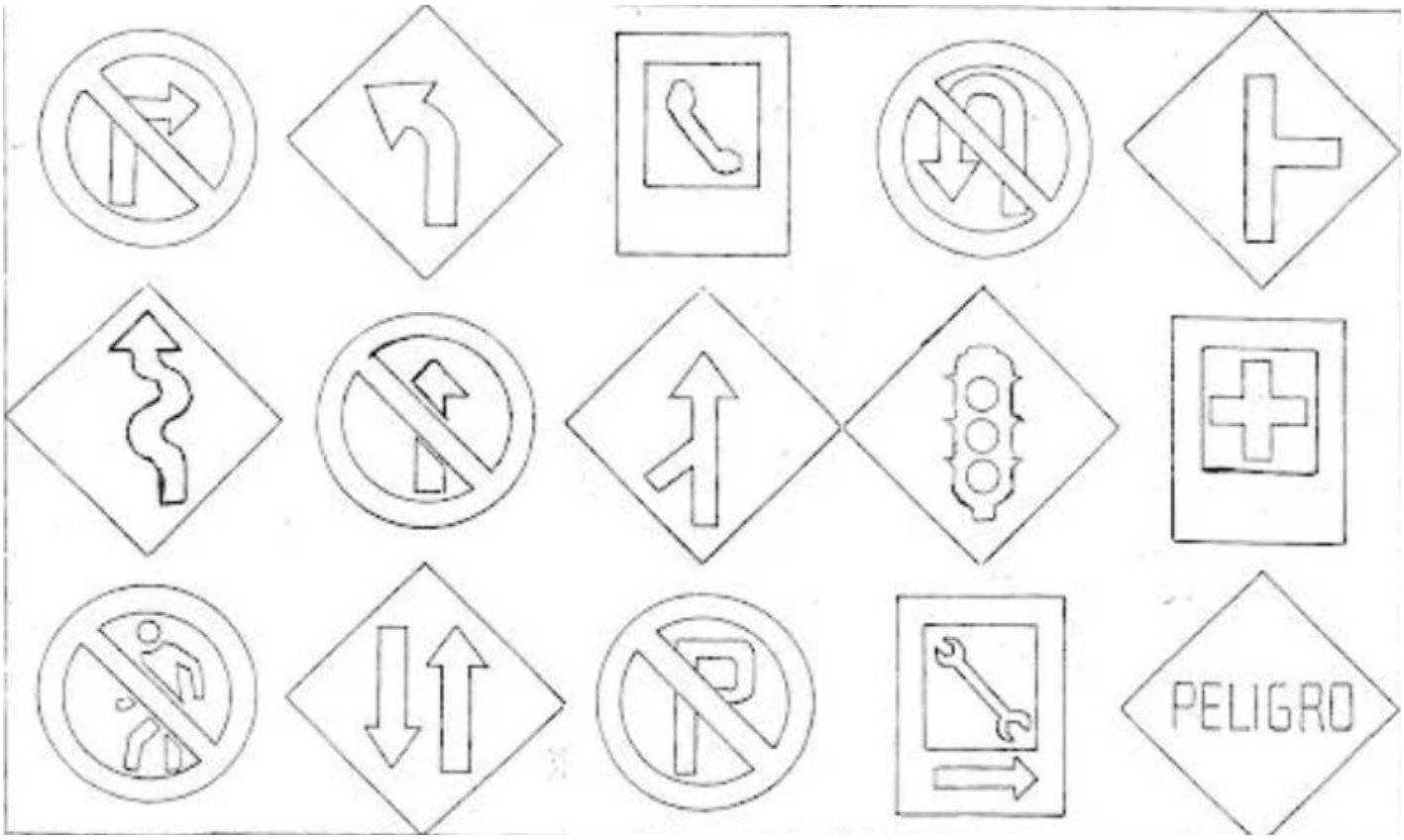

EXPLICO LA FUNCION DE CADA IMAGEN COLOREADA:

1). _____

2). _____

3). _____

4). _____

5). _____

	INSTITUCIÓN EDUCATIVA **COLEGIO GENERAL SANTANDER** **MUNICIPIO DE VILLA DEL ROSARIO** **PROYECTO MOVILIDAD SEGURA** **EDUCACIÓN BÁSICA PRIMARIA, GRADOS 4 Y 5.**					**CÓDIGO** **GAC01** **Fecha de Aprobación:** **31/01/19**	
SEDE ESCOLAR		**GRADO-JORNADA**		**TEMA**	**Señales Preventivas** – Competencia: Asumir la regulación		
ACTIVIDAD	Coloreo las señales preventivas y las explico. Socializo la respuesta.					**FICHA**	04
NOMBRE				**FECHA**			

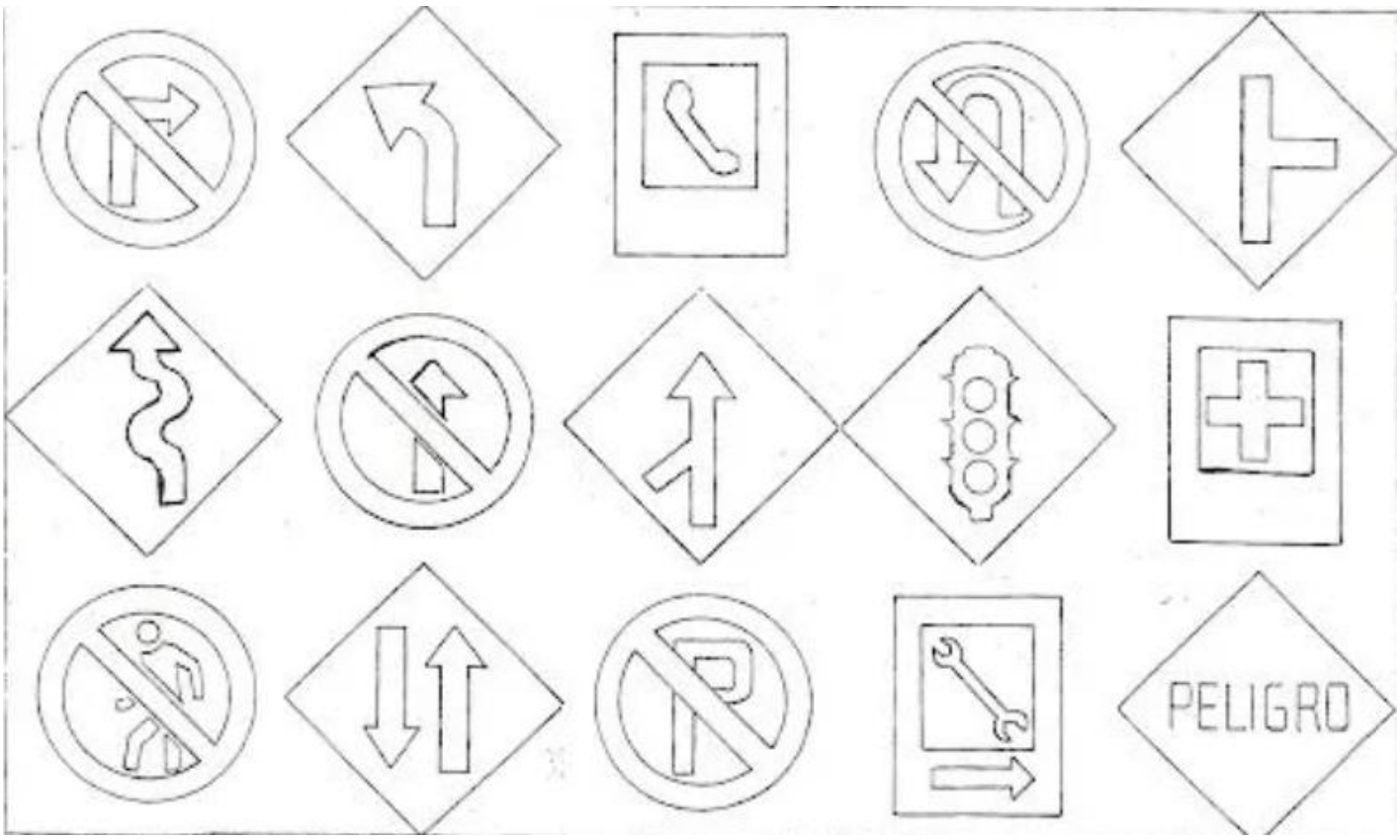

EXPLICO LA FUNCION DE CADA IMAGEN COLOREADA:

1). _____

2). _____

3). _____

4). _____

5). _____

	INSTITUCIÓN EDUCATIVA **COLEGIO GENERAL SANTANDER** **MUNICIPIO DE VILLA DEL ROSARIO** **PROYECTO MOVILIDAD SEGURA** **EDUCACIÓN BÁSICA PRIMARIA, GRADOS 4 Y 5.**					**CÓDIGO** **GAC01** **Fecha de Aprobación:** **31/01/19**	
SEDE ESCOLAR		**GRADO-JORNADA**		**TEMA**	**Señales Informativas** – Competencia: Asumir la regulación		
ACTIVIDAD	Coloreo las señales informativas y las explico. Socializo la respuesta.					**FICHA**	05
NOMBRE				**FECHA**			

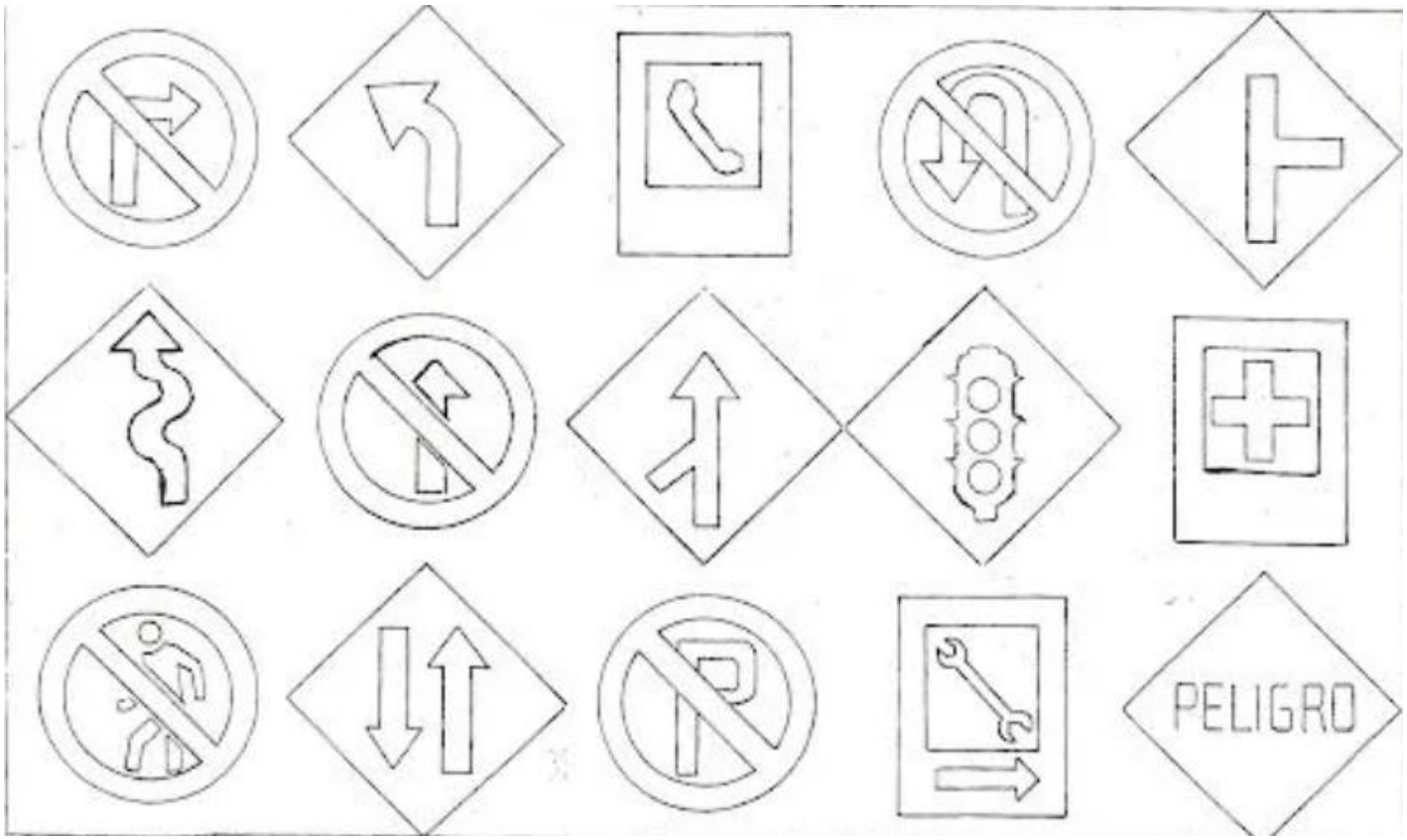

EXPLICO LA FUNCION DE CADA IMAGEN COLOREADA:

1). _____

2). _____

3). _____

4). _____

5). _____

	INSTITUCIÓN EDUCATIVA **COLEGIO GENERAL SANTANDER** **MUNICIPIO DE VILLA DEL ROSARIO** **PROYECTO MOVILIDAD SEGURA** **EDUCACIÓN BÁSICA PRIMARIA, GRADOS 4 Y 5.**					**CÓDIGO** **GAC01** **Fecha de Aprobación:** **31/01/19**	
SEDE ESCOLAR		**GRADO-JORNADA**		**TEMA**	**Ceda el paso –** Competencia: Asumir la regulación.		
ACTIVIDAD	Aplicar témperas o color. Explicar la importancia. Socializo la respuesta.					**FICHA**	06
NOMBRE				**FECHA**			

EXPLICO:

¿Cuándo y por qué el conductor de un vehículo debe ceder el paso?

_____

_____

_____

_____

	INSTITUCIÓN EDUCATIVA **COLEGIO GENERAL SANTANDER** **MUNICIPIO DE VILLA DEL ROSARIO** **PROYECTO MOVILIDAD SEGURA** **EDUCACIÓN BÁSICA PRIMARIA, GRADOS 4 Y 5.**	**CÓDIGO** **GAC01** **Fecha de Aprobación:** **31/01/19**

SEDE ESCOLAR		**GRADO-JORNADA**		**TEMA**	**Señal de pare** – Competencia: Asumir la regulación

ACTIVIDAD	Colorear y explicar la importancia de la señal de pare. Socializo la respuesta.	**FICHA**	07
NOMBRE		**FECHA**	



EXPLICO:

1). ¿Por qué es importante para el conductor de un vehículo hacer el pare?

_____

_____

_____

_____

2). ¿En cuáles sitios he visto ubicada la señal de pare y por qué?

_____

_____

_____

_____

	INSTITUCIÓN EDUCATIVA **COLEGIO GENERAL SANTANDER** **MUNICIPIO DE VILLA DEL ROSARIO** **PROYECTO MOVILIDAD SEGURA** **EDUCACIÓN BÁSICA PRIMARIA, GRADOS 4 Y 5.**						**CÓDIGO** **GAC01** **Fecha de Aprobación:** **31/01/19**
SEDE ESCOLAR		**GRADO-JORNADA**		**TEMA**	**La cebra** – Competencia: Asumir la regulación.		
ACTIVIDAD	Coloreo la cebra vial de blanco y negro; semáforo. Socializo la respuesta.					**FICHA**	08
NOMBRE				**FECHA**			

EXPLICO:

1). ¿Por qué es importante para el peatón cruzar la calzada por la cebra?

_____

_____

2). ¿Cuál luz del semáforo le permite al peatón cruzar por la cebra?

_____

_____

3). ¿Cómo se sienten los niños cruzando por la cebra y por qué?

_____

_____

	INSTITUCIÓN EDUCATIVA **COLEGIO GENERAL SANTANDER** **MUNICIPIO DE VILLA DEL ROSARIO** **PROYECTO MOVILIDAD SEGURA** **EDUCACIÓN BÁSICA PRIMARIA, GRADOS 4 Y 5.**	**CÓDIGO** **GAC01** **Fecha de Aprobación:** **31/01/19**

SEDE ESCOLAR		**GRADO-JORNADA**		**TEMA**	**Invasión de carril** – Competencia: Corresponsabilidad vial
ACTIVIDAD	Analizar la situación presentada en la vía y explicarla. Socialización de las respuestas.			**FICHA**	09
NOMBRE			**FECHA**		

EXPLICO, DESPUES DE ANALIZAR LA SITUACION PRESENTADA:

1). ¿Cuál situación se le presenta al conductor del vehículo 1?

_____

_____

2). ¿Cuál situación se le presenta al conductor del vehículo 2?

_____

_____

3). ¿Cuál situación se le presenta al conductor del vehículo 3?

_____

_____

4). ¿El conductor de cuál vehículo, y por qué, pone en riesgo a los otros dos conductores?

_____

_____

5). ¿Cómo es la línea que divide los dos carriles, y qué indica?

_____

_____

	INSTITUCIÓN EDUCATIVA **COLEGIO GENERAL SANTANDER** **MUNICIPIO DE VILLA DEL ROSARIO** **PROYECTO MOVILIDAD SEGURA** **EDUCACIÓN BÁSICA PRIMARIA, GRADOS 4 Y 5.**	**CÓDIGO** **GAC01** **Fecha de Aprobación:** **31/01/19**

SEDE ESCOLAR		**GRADO-JORNADA**		**TEMA**	**Límites de velocidad** – Competencia: Corresponsabilidad vial
ACTIVIDAD	Coloreo los límites de velocidad y respondo las preguntas . Socializo la respuesta.			**FICHA**	10
NOMBRE			**FECHA**		





EXPLICO

1). ¿Cuál es la intención de los límites de velocidad en la zona urbana?

_____

_____

2). ¿Cuál es la velocidad mínima y máxima en la Autopista Internacional Simón Bolívar?

_____

_____

3). ¿Por qué hay que disminuir la velocidad al transitar un vehículo por una cámara de fotomulta?

_____

_____

	INSTITUCIÓN EDUCATIVA **COLEGIO GENERAL SANTANDER** **MUNICIPIO DE VILLA DEL ROSARIO** **PROYECTO MOVILIDAD SEGURA** **EDUCACIÓN BÁSICA PRIMARIA, GRADOS 4 Y 5.**	**CÓDIGO** **GAC01** **Fecha de Aprobación:** **31/01/19**

SEDE ESCOLAR		**GRADO-JORNADA**		**TEMA**	**Cruzar por sitios prohibidos** – Competencia: Corresponsabilidad vial.

ACTIVIDAD	Analizo las dos imágenes y explico la situación presentada. Socializo la respuesta.	**FICHA**	11
NOMBRE		**FECHA**	

EXPLICO

1). ¿Cuál situación se presenta en la primera imagen?

_____

_____

2). ¿Cuál situación se presenta en la segunda imagen?

_____

_____

3). ¿Qué puedo concluir de las dos situaciones presentadas?

_____

_____

_____

_____

1

2

4). ¿Cuál es la función principal del puente peatonal?

_____

_____

_____

_____

_____

	INSTITUCIÓN EDUCATIVA **COLEGIO GENERAL SANTANDER** **MUNICIPIO DE VILLA DEL ROSARIO** **PROYECTO MOVILIDAD SEGURA** **EDUCACIÓN BÁSICA PRIMARIA, GRADOS 4 Y 5.**						**CÓDIGO** **GAC01** **Fecha de Aprobación:** **31/01/19**
SEDE ESCOLAR		**GRADO-JORNADA**		**TEMA**	**Conductor de bicicleta** – Competencia: Corresponsabilidad vial.		
ACTIVIDAD	Coloreo el ciclista y su medio de transporte. Socializo la respuesta.					**FICHA**	12
NOMBRE				**FECHA**			

EXPLICO

1). Como actor vial, el ciclista, ¿por dónde debe transitar? _____

2). ¿Cuáles elementos protectores, debe utilizar un ciclista? _____

3). ¿Por qué el ciclista debe respetar las señales de tránsito? _____

_____

4). ¿Por cuál lado de la calzada debe transitar el ciclista? _____

5). ¿Qué tipo de ropa debe utilizar el ciclista? _____



	INSTITUCIÓN EDUCATIVA **COLEGIO GENERAL SANTANDER** **MUNICIPIO DE VILLA DEL ROSARIO** **PROYECTO MOVILIDAD SEGURA** **EDUCACIÓN BÁSICA PRIMARIA, GRADOS 4 Y 5.**					**CÓDIGO** **GAC01** **Fecha de Aprobación:** **31/01/19**	
SEDE ESCOLAR		**GRADO-JORNADA**		**TEMA**	**El respeto**: la llave que abre el transporte público – Competencia: Corresponsabilidad vial.		
ACTIVIDAD	Coloreo los pasajeros. Socializo la respuesta.					**FICHA**	13
NOMBRE			**FECHA**				

EXPLICO

1). ¿Los niños hacen buen uso del transporte? ____ ¿Por qué? _____
_____

2). ¿Los niños son respetuosos de las normas en el transporte público? ___ ¿Por qué? _____

3). ¿Por qué es importante el respeto? _____
_____

4). ¿Cómo actor vial, soy respetuoso de las normas? ___ ¿Por qué? _____
_____

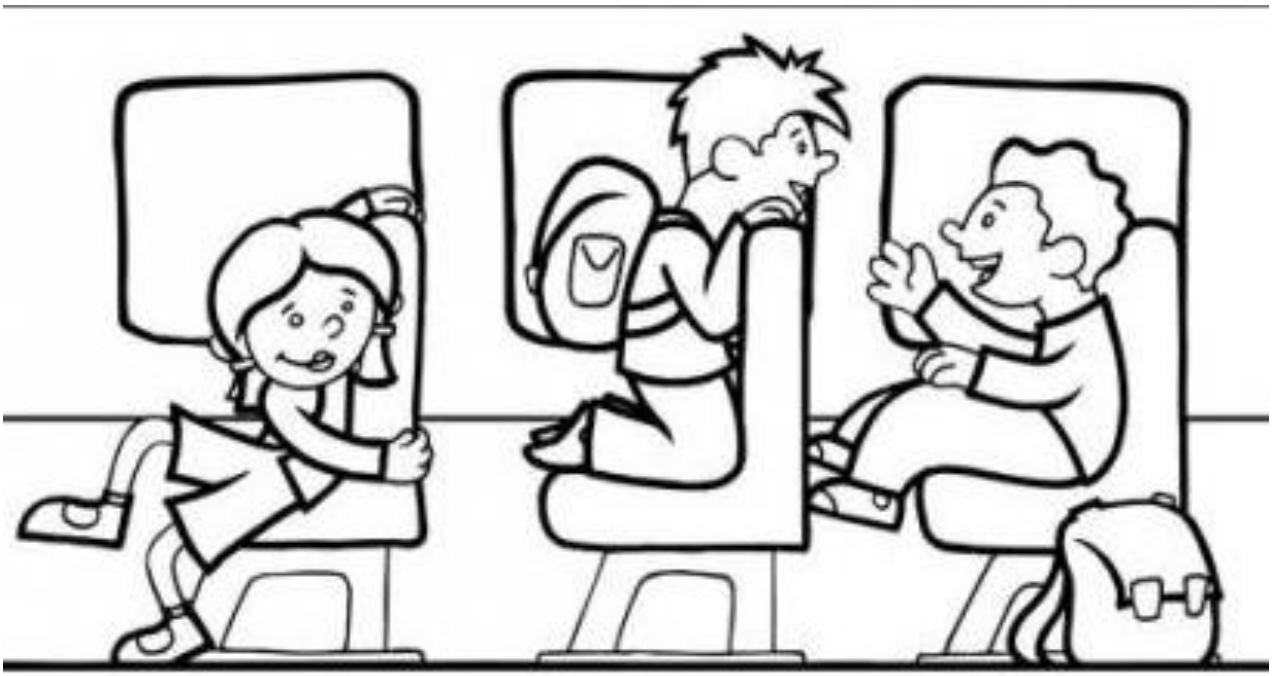

	INSTITUCIÓN EDUCATIVA **COLEGIO GENERAL SANTANDER** **MUNICIPIO DE VILLA DEL ROSARIO** **PROYECTO MOVILIDAD SEGURA** **EDUCACIÓN BÁSICA PRIMARIA, GRADOS 4 Y 5.**					**CÓDIGO** **GAC01** **Fecha de Aprobación:** **31/01/19**	
SEDE ESCOLAR		**GRADO-JORNADA**		**TEMA**	**Distracción en la vía como peatón** – Competencia: Valoración en la movilidad del riesgo y la vulnerabilidad.		
ACTIVIDAD	Coloreo el peatón. Socializo la respuesta.					**FICHA**	14
NOMBRE				**FECHA**			

EXPLICO

1). El peatón de la imagen, ¿está seguro en la vía por donde transita? ___ ¿Por qué? _____

2). ¿Cuál peligro puede enfrentar el peatón, caminando distraído? _____
_____

3). ¿Como peatón, alguna vez me he sentido vulnerable? ___ ¿Por qué? _____
_____

4). ¿Como peatón, mi mirada hacia donde debe estar dirigida? _____
_____

	INSTITUCIÓN EDUCATIVA **COLEGIO GENERAL SANTANDER** **MUNICIPIO DE VILLA DEL ROSARIO** **PROYECTO MOVILIDAD SEGURA** **EDUCACIÓN BÁSICA PRIMARIA, GRADOS 4 Y 5.**					**CÓDIGO** **GAC01** **Fecha de Aprobación:** **31/01/19**	
SEDE ESCOLAR		**GRADO-JORNADA**		**TEMA**	**Comportamientos inseguros de los peatones en la vía pública** – Competencia: Valoración en la movilidad del riesgo y la vulnerabilidad.		
ACTIVIDAD	Coloreo los peatones. Socializo la respuesta.					**FICHA**	15
NOMBRE				**FECHA**			



EXPLICO

1). ¿Qué sucedió con los niños peatones de la imagen? _____
_____

2). ¿Por qué se presentó la situación de la imagen? _____
_____

3). ¿Por qué la expresión de angustia de los dos peatones adultos? _____
_____

4). ¿Por qué el conductor del vehículo se muestra iracundo? _____
_____

	INSTITUCIÓN EDUCATIVA **COLEGIO GENERAL SANTANDER** **MUNICIPIO DE VILLA DEL ROSARIO** **PROYECTO MOVILIDAD SEGURA** **EDUCACIÓN BÁSICA PRIMARIA, GRADOS 4 Y 5.**	**CÓDIGO** **GAC01** **Fecha de Aprobación:** **31/01/19**

SEDE ESCOLAR		**GRADO-JORNADA**		**TEMA**	**Cruzar la vía**: Observando cada uno de los lados – Competencia: Valoración en la movilidad del riesgo y la vulnerabilidad

ACTIVIDAD	Interpreto las imágenes. Socializo la respuesta.	**FICHA**	16
NOMBRE		**FECHA**	

IMAGEN 1

IMAGEN 2

IMAGEN 3

IMAGEN 4

EXPLICO:

1). ¿Qué ocurre en la imagen 1? _____

_____

2). ¿Qué ocurre en la imagen 2? _____

_____

3). ¿Qué ocurre en la imagen 3? _____

_____

4). ¿Qué ocurre en la imagen 4? _____

_____

	INSTITUCIÓN EDUCATIVA **COLEGIO GENERAL SANTANDER** **MUNICIPIO DE VILLA DEL ROSARIO** **PROYECTO MOVILIDAD SEGURA** **EDUCACIÓN BÁSICA PRIMARIA, GRADOS 4 Y 5.**	**CÓDIGO** **GAC01** **Fecha de Aprobación:** **31/01/19**

SEDE ESCOLAR		**GRADO-JORNADA**		**TEMA**	**Puntos cardinales**– Competencia: Comprensión del entorno
ACTIVIDAD	Coloreo la rosa de los vientos y escribo los puntos cardinales. Socializo la respuesta.			**FICHA**	17
NOMBRE			**FECHA**		

SUR

ESTE

OESTE

NORTE

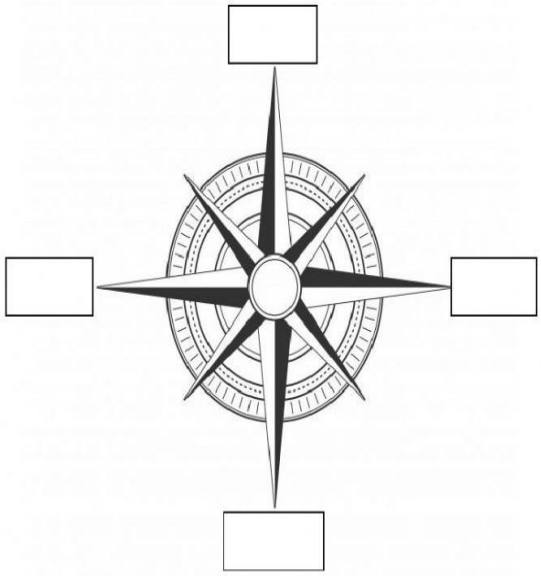

EXPLICO:

1. En Villa del Rosario, ¿las carreras van de cuál punto cardinal a cuál? _____
_____

2. En Villa del Rosario, ¿las calles van de cuál punto cardinal a cuál? _____
_____

3. ¿Cuál conductor tiene la prelación o preferencia al transitar por una vía?
_____

4. ¿Por qué es importante para el conductor que transita por la calle hacer el pare?
_____

5. ¿Cuál es la dirección de mis Sede Escolar? _____
_____

6. ¿Cuál es la dirección de mi casa? _____
_____

	INSTITUCIÓN EDUCATIVA **COLEGIO GENERAL SANTANDER** **MUNICIPIO DE VILLA DEL ROSARIO** **PROYECTO MOVILIDAD SEGURA** **EDUCACIÓN BÁSICA PRIMARIA, GRADOS 4 Y 5.**	**CÓDIGO** **GAC01** **Fecha de Aprobación:** **31/01/19**

SEDE ESCOLAR		**GRADO-JORNADA**		**TEMA**	**Zonas peatonales–** Competencia: Movilidad idónea
ACTIVIDAD	Coloreo las zonas destinadas a los peatones. Socializo la respuesta.			**FICHA**	18
NOMBRE			**FECHA**		



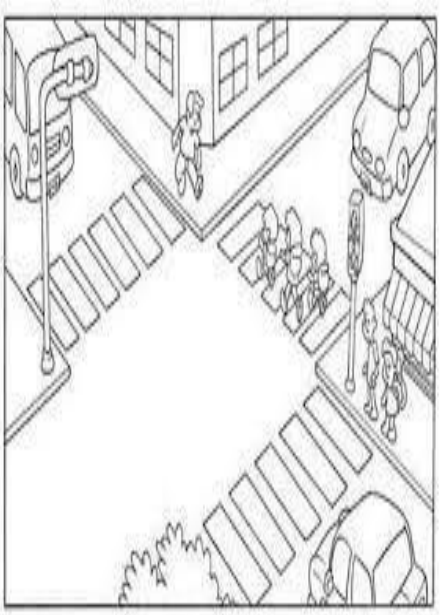

EXPLICO:

1. ¿Por qué se dice que los peatones son vulnerables? _____
_____

2. ¿Cómo debe actuar un peatón cuando se encuentra ante un semáforo? _____
_____
_____
_____

3. ¿Cuál es el sitio más seguro para que un peatón cruce la calzada? ¿Por qué?
_____

4. En una autopista por, ¿Por dónde debe cruzar el peatón? ¿Por qué?
_____
_____

5. En Villa del Rosario, ¿cuáles puentes peatonales conozco? ¿Son utilizados por los peatones? ¿Por qué? _____
_____
_____
_____

	INSTITUCIÓN EDUCATIVA **COLEGIO GENERAL SANTANDER** **MUNICIPIO DE VILLA DEL ROSARIO** **PROYECTO MOVILIDAD SEGURA** **EDUCACIÓN BÁSICA PRIMARIA, GRADOS 4 Y 5.**	**CÓDIGO** **GAC01** **Fecha de Aprobación:** **31/01/19**

SEDE ESCOLAR		**GRADO-JORNADA**		**TEMA**	**Visión periférica–** Competencia: Movilidad idónea
ACTIVIDAD	Analizo la imagen y explico. Socializo la respuesta.			**FICHA**	19
NOMBRE		**FECHA**			

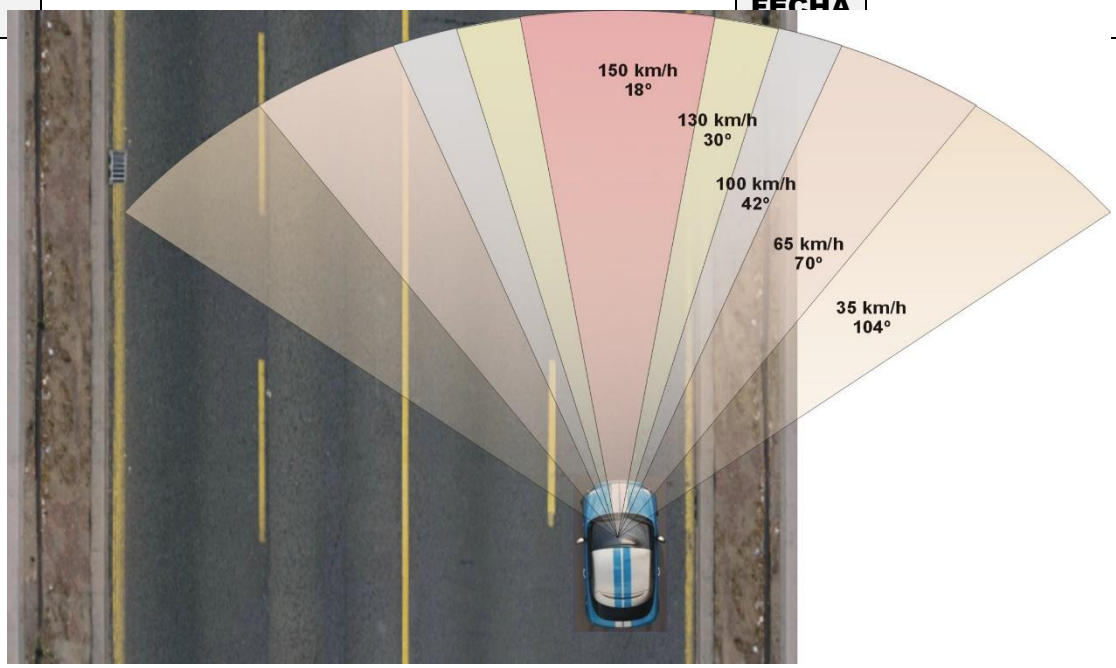

La visión periférica permite ver nuestro entorno en general, puede abarcar casi 180 grados y está relacionada con la localización y el reconocimiento de los objetos de nuestro alrededor.

EXPLICO:

1. ¿A cuántos km/h, tiene el conductor del vehículo un mayor grado de observación de su entorno? ¿Por qué? _____
   _____
2. ¿A cuántos km/h, tiene el conductor del vehículo un menor grado de observación de su entorno? ¿Por qué? _____
   _____
3. ¿Cuál puede ser una velocidad promedio que le permita al conductor tener una mejor observación de su entorno? ¿Por qué? _____
   _____
4. Para evitar un posible accidente, ¿qué debe hacer el conductor? _____
   _____
   _____

	INSTITUCIÓN EDUCATIVA **COLEGIO GENERAL SANTANDER** **MUNICIPIO DE VILLA DEL ROSARIO** **PROYECTO MOVILIDAD SEGURA** **EDUCACIÓN BÁSICA PRIMARIA, GRADOS 4 Y 5.**	**CÓDIGO** **GAC01** **Fecha de Aprobación:** **31/01/19**

SEDE ESCOLAR		**GRADO-JORNADA**		**TEMA**	**Cinturón de seguridad–** Competencia: Movilidad idónea
ACTIVIDAD	Coloreo los pasajeros y remarco el cinturón de seguridad. Socializo la respuesta.			**FICHA**	20
NOMBRE			**FECHA**		

EXPLICO:

1). ¿Por qué los pasajeros que van en el asiento trasero deben usar el cinturón de seguridad? _____

_____

2). ¿Quién y por qué, debe el ordenar el uso del cinturón de seguridad en el vehículo? _____

_____

3). ¿Por qué el conductor del vehículo debe usar el cinturón de seguridad?

_____

_____

4). ¿Cuál puede ser el beneficio de utilizar el cinturón de seguridad?

_____

_____

5). Los ocupantes de un vehículo, ¿deben utilizar el cinturón de seguridad sólo cuando vean un agente de tránsito o un policía? _____

_____

Referencias

Agencia Nacional de Seguridad Vial. https://ansv.gov.co/es/escuela

Asamblea General de las Naciones Unidas. (2 de septiembre del 2020). Resolución 74/299: Mejoramiento de la seguridad vial en el mundo. Recuperado de https://bit.ly/38uSGqV

Congreso de Colombia. (30 de diciembre del 2011). Ley 1503 de 2011: por la cual se promueve la formación de hábitos, comportamientos y conductas seguros en la vía y se dictan otras disposiciones. DO: 48 298. Recuperado de https://bit.ly/2P6arlD

Congreso de Colombia. (27 de diciembre del 2013). Ley 1702 de 2013: por la cual se crea la agencia nacional de seguridad vial y se dictan otras disposiciones. DO: 49 016. Recuperado de https://bit.ly/39FxHk4

Draisin, N., Silverman, A., Fundación FIA, González, F., Lambrosquini, F., Silva, M., Zugarramurdi, F., Fundación Gonzalo Rodríguez. (2018). Calles para la vida. Trayectos seguros y saludables para los niños de América Latina y el Caribe. Recuperado de https://uni.cf/335qDM3

Ministerio de Transporte. (2015). Plan Nacional de Seguridad Vial. Colombia 2011-2021 (2.a ed.). Recuperado de https://bit.ly/2X4yyp6

Organización Mundial de la Salud (OMS). (2015). Diez estrategias para preservar la seguridad de los niños en las carreteras. Autor. Recuperado de https://bit.ly/2Excc9u